RÉPUBLIQUE FRANÇAISE
Liberté
Égalité
Fraternité

OFB
OFFICE FRANÇAIS DE LA BIODIVERSITÉ

Bilan de l'activité de contrôle Agrainage

Côte-d'Or

Période : 01/01/2025 au 05/02/2026

Données OSCEAN & PVe OFB

Office français de la biodiversité
SD de la Côte-d'Or – www.ofb.gouv.fr

Sommaire

I. Contrôles agrainage

II. Infractions PVe

III. Procédures judiciaires (PEJ)

IV. Synthèse par zone

V. Cartographie

Annexes

I. Contrôles agrainage

Contrôles liés à l'agrainage identifiés dans les points de contrôle OSCEAN (champ « nom_dossie » contenant « agrain »).

70	37	52.9%
Contrôles agrainage	Infractions	Taux d'infraction

Tableau 1 : Résultats des contrôles agrainage (département)

Résultat	Nombre	Taux
Infraction	37	52.9%
Conforme	31	44.3%
Manquement	1	1.4%
Inconnu	1	1.4%

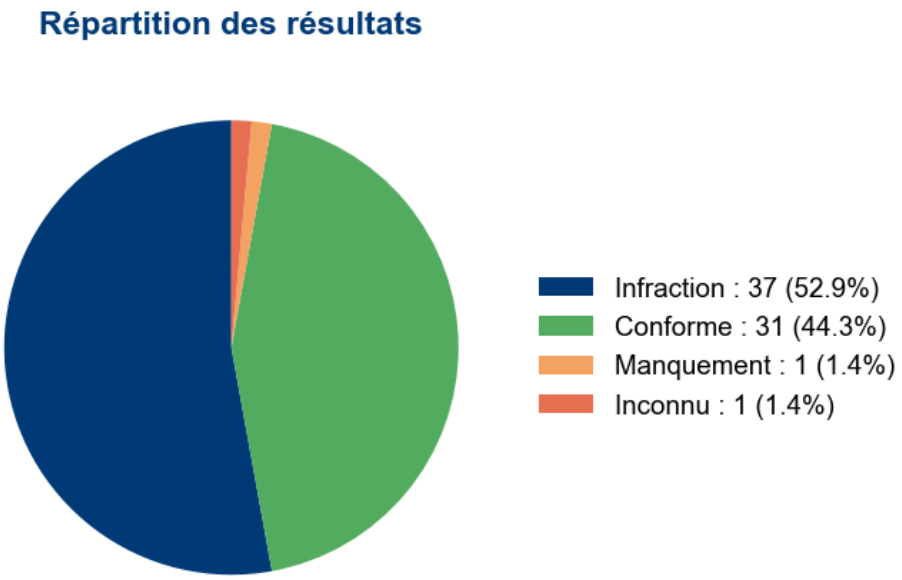

Tableau 2 : Contrôles agrainage par zone

Zone	Nb contrôles	Nb conformes	Nb infractions	Taux infraction
Département	70	33	37	52.9%
Zone TUB	48	24	24	50.0%
PNF	11	5	6	54.5%

Répartition par zone : Département : 70 contrôle(s), 37 infraction(s) (52.9%) ; Zone TUB : 48 contrôle(s), 24 infraction(s) (50.0%) ; PNF : 11 contrôle(s), 6 infraction(s) (54.5%).

Source : OSCEAN, contrôles agrainage du 01/01/2025 au 05/02/2026, département 21.

II. Infractions PVe

Infractions relevées par Procès-Verbal électronique (PVe) pour le NATINF 27742 (agrainage) en Côte-d'Or.

32

PVe agrainage

Tableau 3 : PVe agrainage par zone

Zone	Nombre de PVe
Département	32
Zone TUB	19
PNF	3

Répartition : Département : 32 PVe ; Zone TUB : 19 PVe ; PNF : 3 PVe.

Source : Stats PVe OFB au 05/02/2026, NATINF 27742, département 21.

III. Procédures judiciaires (PEJ)

Infractions ayant fait l'objet d'une procédure d'enquête judiciaire pour les NATINF 27742 ou 25001 en Côte-d'Or.

2	106 j
PEJ agrainage	Durée moy. PEJ

Tableau 4 : PEJ agrainage par zone

Zone	Nombre de PEJ
Département	2
Zone TUB	1
PNF	1

Répartition : Département : 2 PEJ ; Zone TUB : 1 PEJ ; PNF : 1 PEJ.

Source : OSCEAN, procédures judiciaires, NATINF 27742/25001, département 21.

IV. Synthèse par zone

Tableau croisé des différentes sources d'infractions d'agrainage par périmètre géographique (département, zone TUB, PNF).

Tableau 5 : Synthèse agrainage par zone et source

Zone	Ctrl total	Ctrl infractions	PVe	PEJ
Département	70	37	32	2
PNF	11	6	3	1
Zone TUB	48	24	19	1

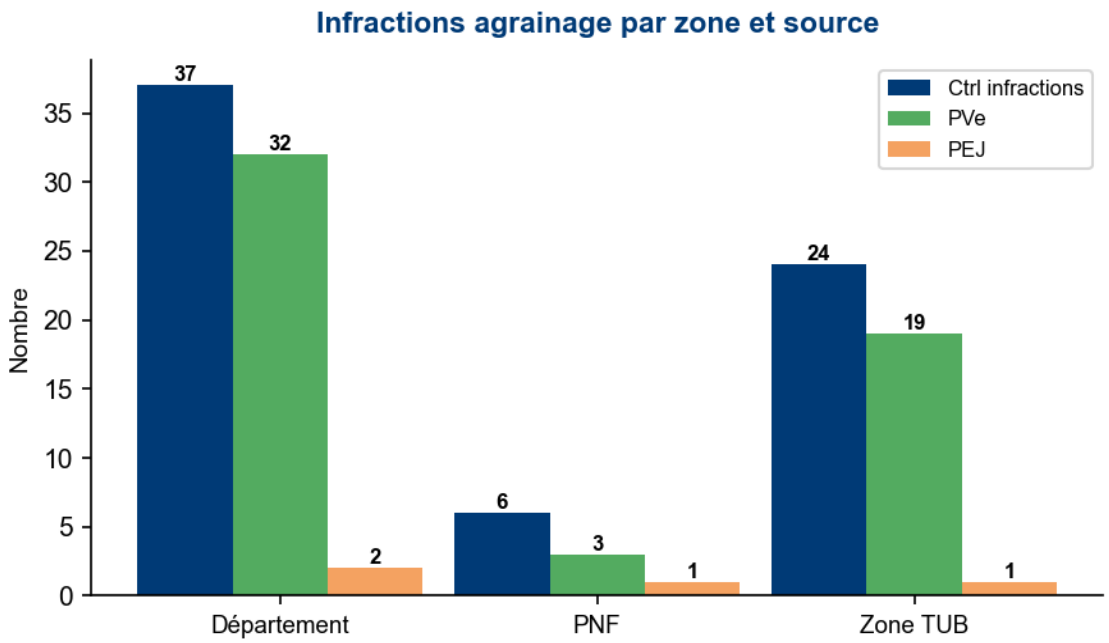
Infractions agrainage par zone et source
Nombre
0
5
10
15
20
25
30
35
37
32
2
6
3
1
24
19
1
Département
PNF
Zone TUB
Ctrl infractions
PVe
PEJ

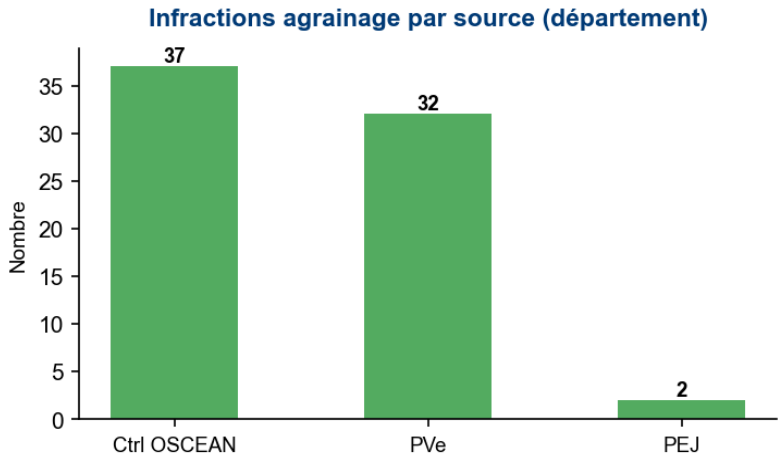
Infractions agrainage par source (département)
Nombre
0
5
10
15
20
25
30
35
37
32
2
Ctrl OSCEAN
PVe
PEJ

V. Cartographie

Agrainage illicite (NATINF 27742 et 25001) — Côte-d'Or

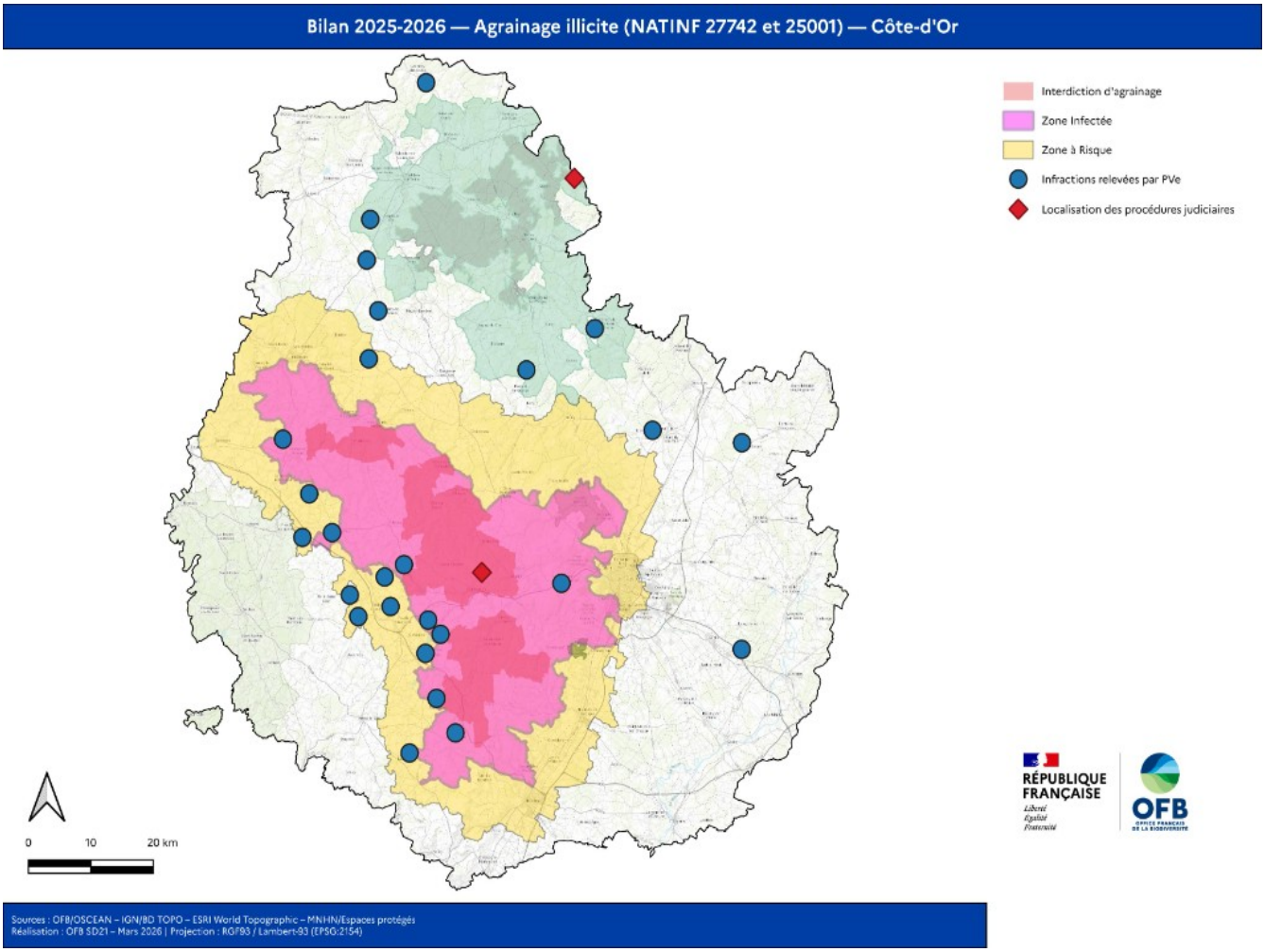

Sources : OFB/OSCEAN – IGN/BD TOPO – ESRI World Topographic – MNHN/Espaces protégés. Réalisation : OFB SD21 – Mars 2026.

Annexes

Méthodologie

Période d'analyse : du 01/01/2025 au 05/02/2026.
Périmètre : département de la Côte-d'Or (21).
Sources : OSCEAN (points de contrôle, PEJ) et PVe OFB.
Contrôles agrainage : points de contrôle dont le champ « nom_dossie » contient « agrain ».
PVe agrainage : NATINF 27742.
PEJ agrainage : NATINF 27742 ou 25001.
Zone TUB : communes de la zone TUB (source : tub_communes.csv).
PNF : communes situées dans le périmètre du Parc national de forêts.

Glossaire

Abréviation	Signification
DC	Dossier de contrôle
NATINF	Nature d'infraction (nomenclature nationale)
OSCEAN	Outil pour la surveillance et le contrôle eau et nature (application nationale)
PEJ	Procédure d'enquête judiciaire
PNF	Parc national de forêts
PVe	Procès-verbal électronique
TUB	Zone délimitée par l'arrêté préfectoral « Tuberculose bovine »